Raport Rekomendacji Tras Turystycznych

Twoje preferencje:

- Minimalna temperatura: 0.0°C
- Maksymalna temperatura: 100.0°C
- Minimalna długość trasy: 0.0 km
- Maksymalna długość trasy: 100.0 km
- Minimalna trudność: 1.0/5
- Maksymalna trudność: 5.0/5
- Region: Tatry

Na podstawie Twoich preferencji znaleziono: • Liczba znalezionych tras: 3 • Średnia długość trasy: 8.6 km • Średnia trudność: 3.2/5

Wygenerowano: 11.06.2025 00:32

Spis treści

1. Profile wysokościowe tras
2. Szczegółowe opisy rekomendowanych tras
3. Analiza porównawcza
4. Analiza sezonowości
5. Tabela zbiorcza
6. Aneks - Dane źródłowe

1. Profile wysokościowe tras

Profil wysokościowy - Dolina Pięciu Stawów

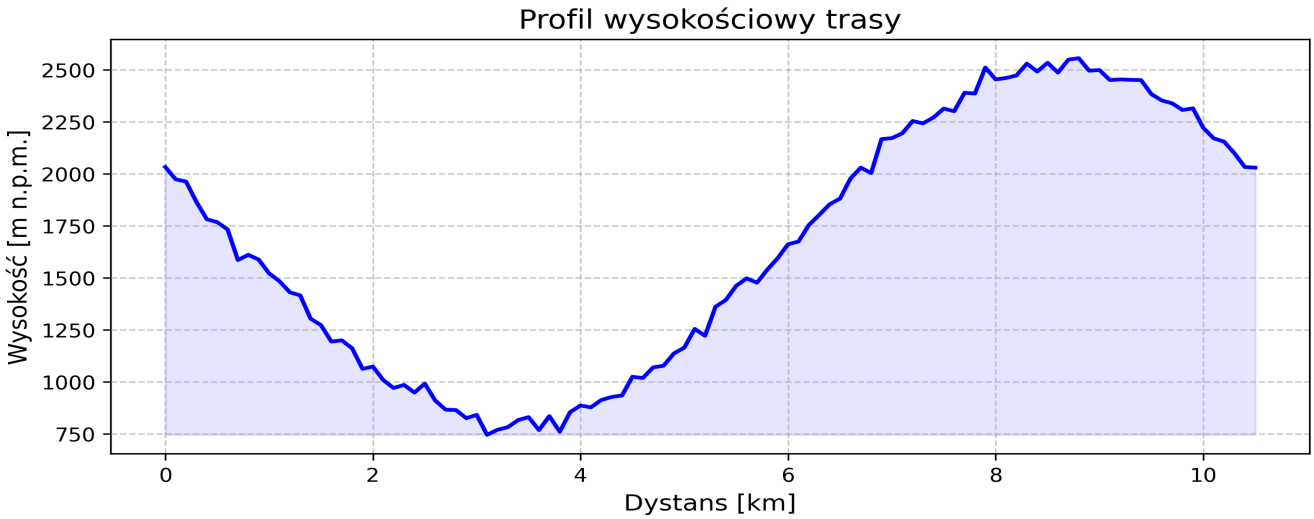

Trasa rozpoczyna się na wysokości 2033m n.p.m. i kończy na wysokości 2030m n.p.m. Najniższy punkt: 746m n.p.m. Najwyższy punkt: 2556m n.p.m. Całkowity dystans: 10.5km

Profil wysokościowy - Szlak na Giewont

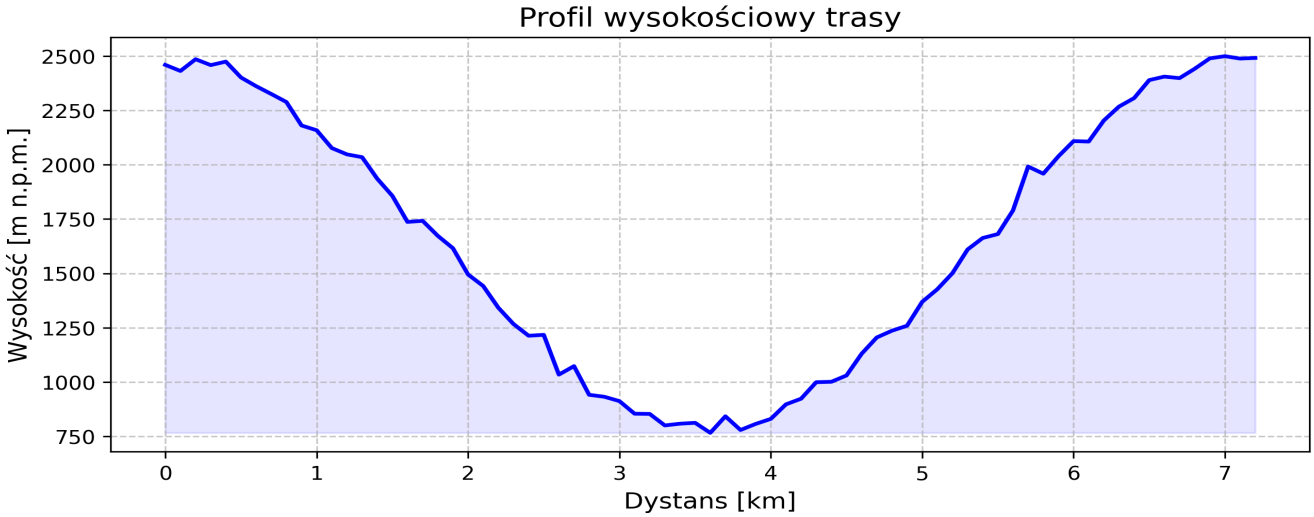

Trasa rozpoczyna się na wysokości 2460m n.p.m. i kończy na wysokości 2492m n.p.m. Najniższy punkt: 766m n.p.m. Najwyższy punkt: 2500m n.p.m. Całkowity dystans: 7.2km

Profil wysokościowy - Droga na Morskie Oko

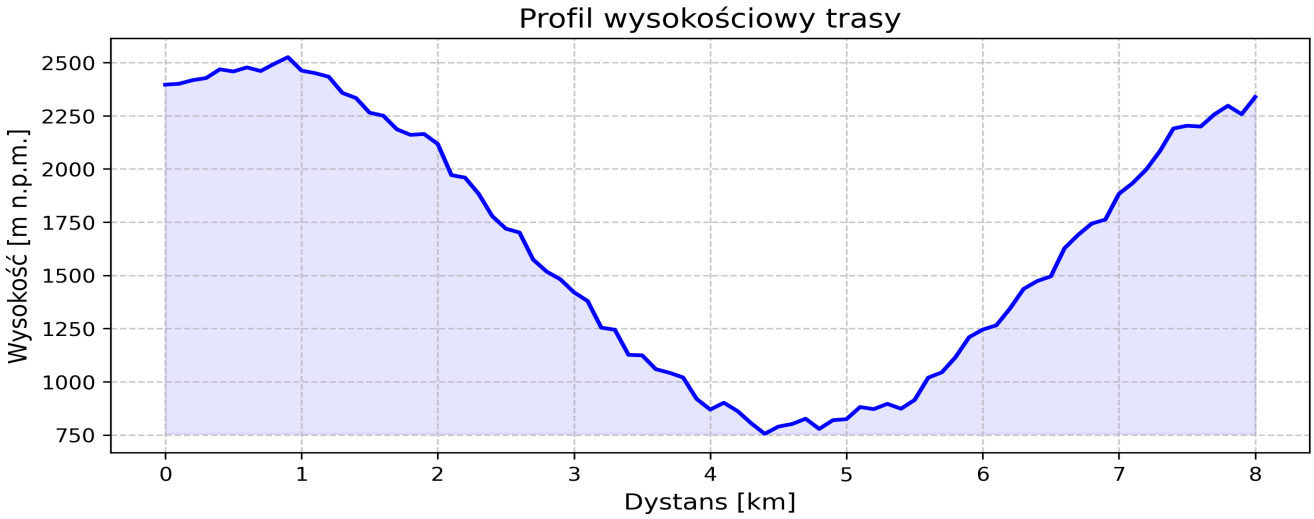

Trasa rozpoczyna się na wysokości 2396m n.p.m. i kończy na wysokości 2338m n.p.m. Najniższy punkt: 755m n.p.m. Najwyższy punkt: 2525m n.p.m. Całkowity dystans: 8.0km

2. Szczegółowe opisy rekomendowanych tras

3. Analiza porównawcza

3.1. Porównanie długości tras

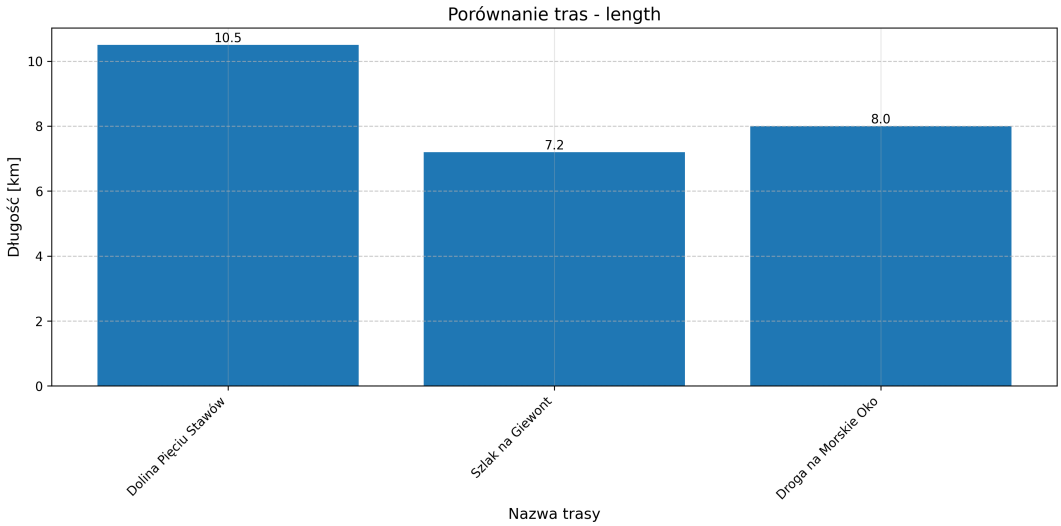

3.2. Rozkład kategorii tras

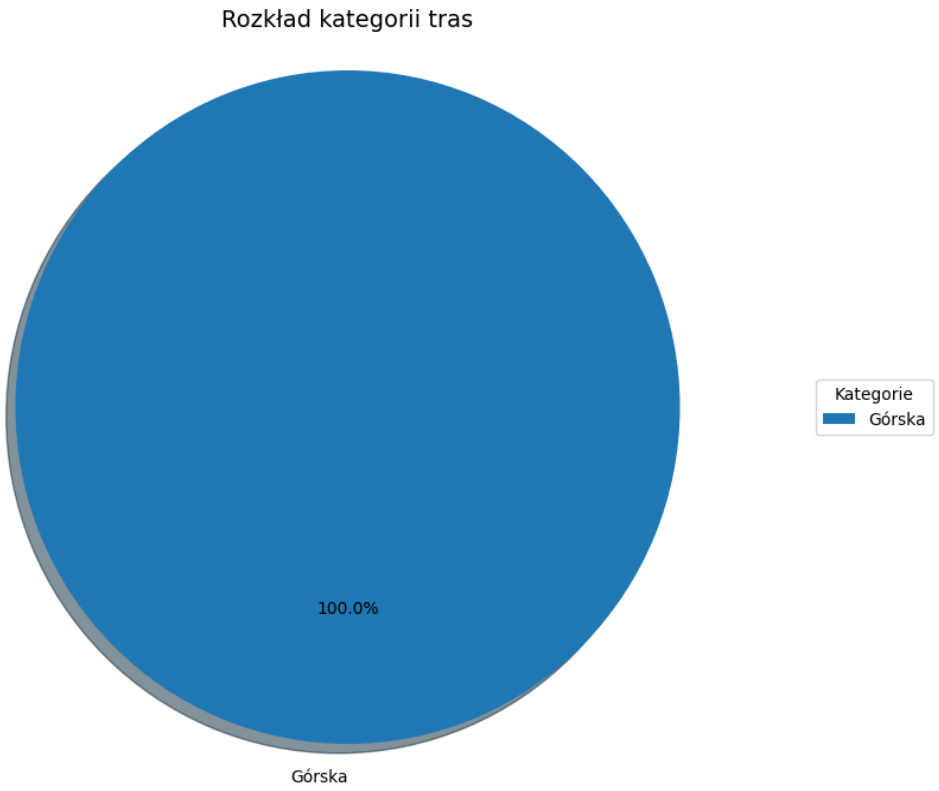

3.3. Opinie użytkowników

Dolina Pięciu Stawów

Parametr	Wartość
Długość	b/d km
Czas przejścia	4:30:00

Przewyższenie	b/d m
Trudność	3.5
Ocena	★★★★ (4.5/5)

Szlak na Giewont

Parametr	Wartość
Długość	b/d km
Czas przejścia	3:45:00
Przewyższenie	b/d m
Trudność	4.0
Ocena	★★★★ (4.5/5)

Droga na Morskie Oko

Parametr	Wartość
Długość	b/d km
Czas przejścia	2:30:00
Przewyższenie	b/d m
Trudność	2.0
Ocena	★★★★ (4.666666666666667/5)

4. Analiza sezonowości

Mapa ciepła popularności tras w różnych miesiącach

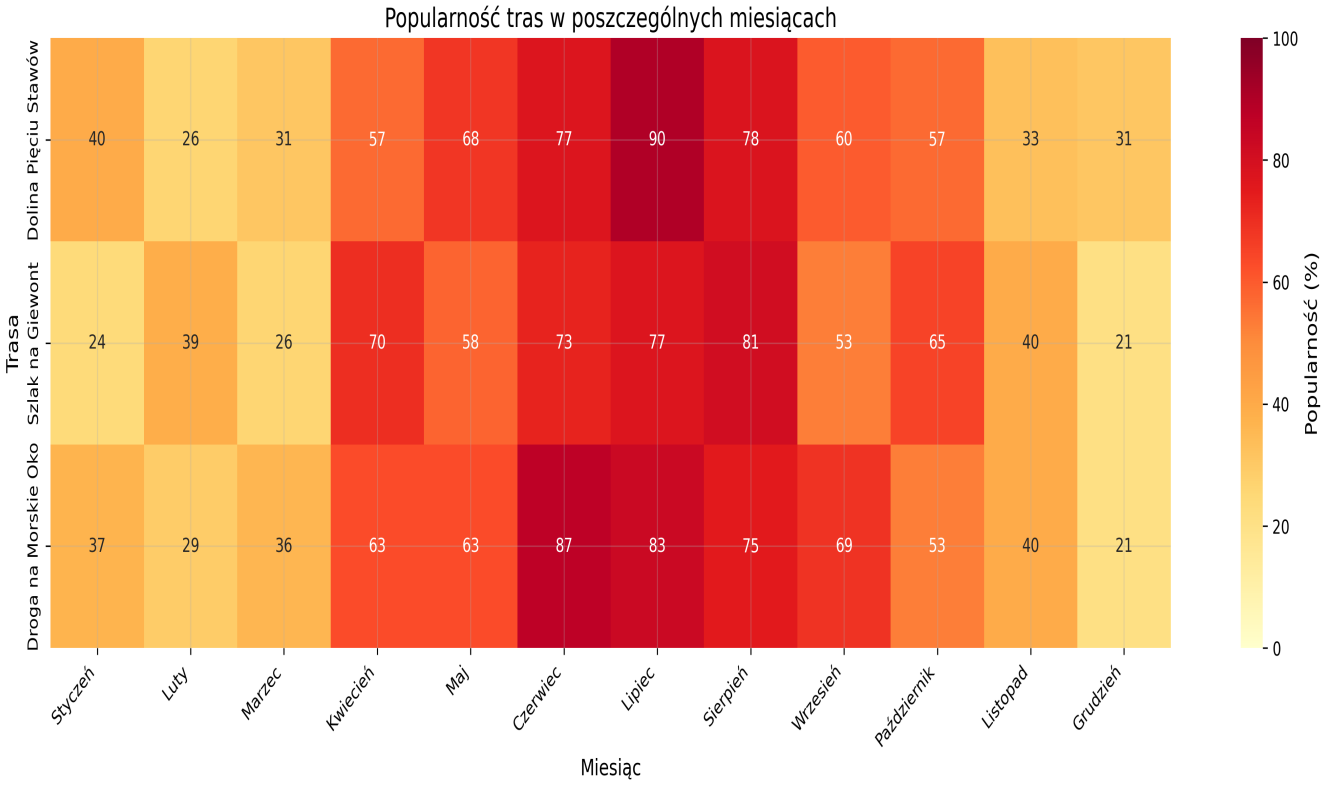

Analiza sezonowości pokazuje zróżnicowaną dostępność tras w zależności od regionu i pory roku: • Okres letni (czerwiec-sierpień) oferuje najlepsze warunki do wędrówek we wszystkich regionach • Wiosna i jesień (kwiecień-maj, wrzesień-październik) to również dobry czas na większość tras • W okresie zimowym (listopad-marzec) dostępność jest ograniczona, szczególnie w wysokich górach • Trasy nizinne i w niższych partiach gór są dostępne przez cały rok

Aktualne warunki pogodowe

Region: Tatry • Temperatura: 23.4°C (min: 18.3°C, max: 31.6°C) • Opady: 2.4 mm • Zachmurzenie: 66.0% • Indeks komfortu: 85.8/100

5. Tabela zbiorcza

Nazwa	Długość	Czas	Trudność	Ocena	Sezon
Dolina Pięciu Stawów	10.5 km	4:30:00	3.5	4.5/5.0	Cały rok
Szlak na Giewont	7.2 km	3:45:00	4.0	4.5/5.0	Cały rok
Droga na Morskie Oko	8.0 km	2:30:00	2.0	4.7/5.0	Cały rok

6. Aneks - Źródła danych

W tej sekcji przedstawiono źródła danych wykorzystanych do przygotowania raportu. Wszystkie dane zostały pozyskane z wiarygodnych źródeł i są regularnie aktualizowane.

6.1. Źródła danych pogodowych

Typ danych	Źródło	Uwagi
Temperatura i opady	OpenWeatherMap API	Dane aktualizowane co godzinę
Prognoza pogody	Met.no Weather API	7-dniowa prognoza pogody
Historyczne dane pogodowe	IMGW-PIB	Archiwalne dane meteorologiczne

6.2. Źródła danych geograficznych

Typ danych	Źródło	Uwagi
Mapy i trasy	OpenStreetMap	Dane społecznościowe
Profile wysokościowe	SRTM (NASA)	Rozdzielczość 30m
Punkty POI	OpenStreetMap + własna baza	Aktualizowane miesięcznie
Granice parków narodowych	GDOŚ	Dane oficjalne

6.3. Dane o trudności i komforcie tras

Oceny trudności i komfortu tras są obliczane na podstawie następujących źródeł: • Opinie użytkowników z portali turystycznych • Dane techniczne trasy (nachylenie, rodzaj nawierzchni) • Oceny przewodników górskich • Statystyki wypadków i interwencji GOPR/TOPR Wszystkie oceny są normalizowane do skali 1-5 i regularnie weryfikowane przez ekspertów.

6.4. Częstotliwość aktualizacji danych

Typ danych	Częstotliwość aktualizacji
Dane pogodowe	Co godzinę
Dane geograficzne	Co miesiąc
Oceny użytkowników	W czasie rzeczywistym
Weryfikacja ekspercka	Co kwartał
Dane o wypadkach	Co tydzień